חוק התכנון והבניה, התשכ"ה- 1965
הועדה הארצית לתכנון ולבניה של תשתיות לאומיות

תת"ל 33

מסילה רביעית באיילון
קטע תי"א מרכז-לוד

תכנית לתשתית לאומית

נספח תנועה-כביש מס'1

גליון מס': 2 מתוך 2
קנ"מ : 2,500 : 1

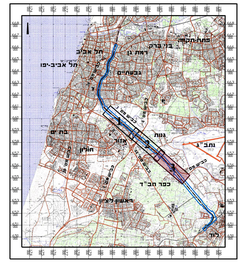
מחוז: תל אביב,מרכז

מרחבי תכנון מקומיים:
- ועדה מקומית תל אביב-יפו
- ועדה מקומית רמת גן
- ועדה מקומית נבטתיים
- מרחב תכנון מחוזי-מקומי (מחוז ת"א)
- ועדה מרחבית אזור יהודה-אזור
- ועדה מרחבית מצפה אפק
- ועדה מקומית עמק לוד
- ועדה מקומית לוד

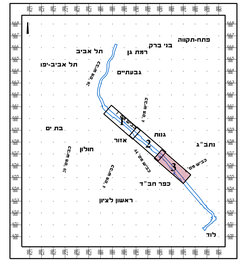
חותמת מוסד התכנון :

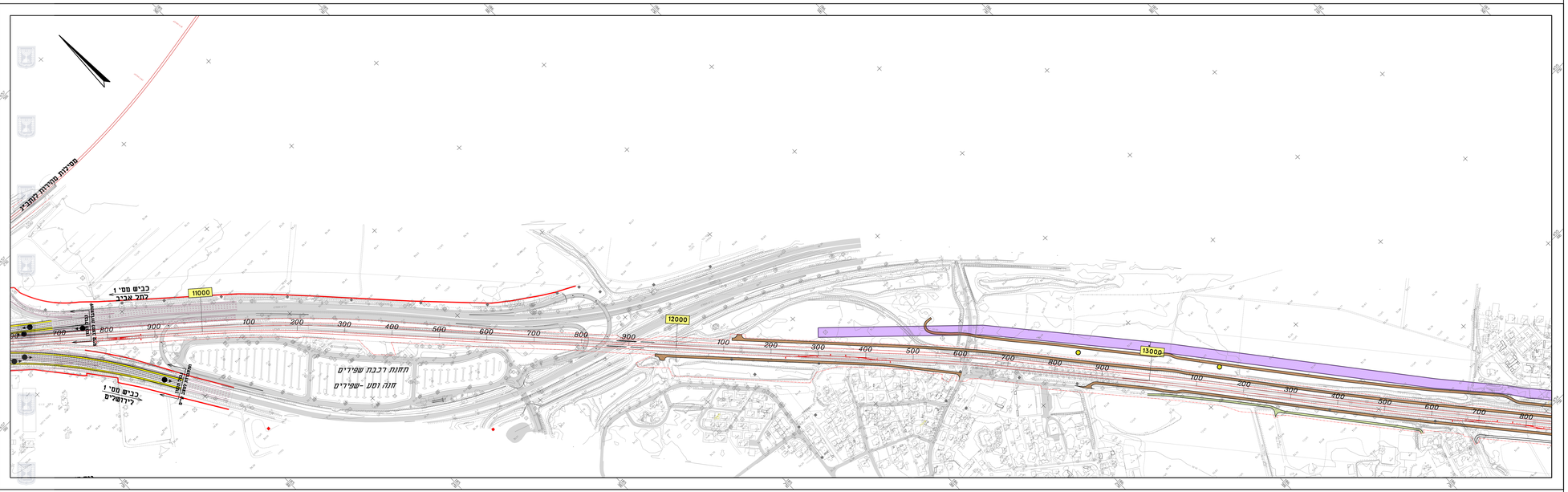
שרב: אישור תכנית מהדורה: 06 תאריך: 25.04.2018

תרשים סביבה :
קנ"מ 100,000 : 1

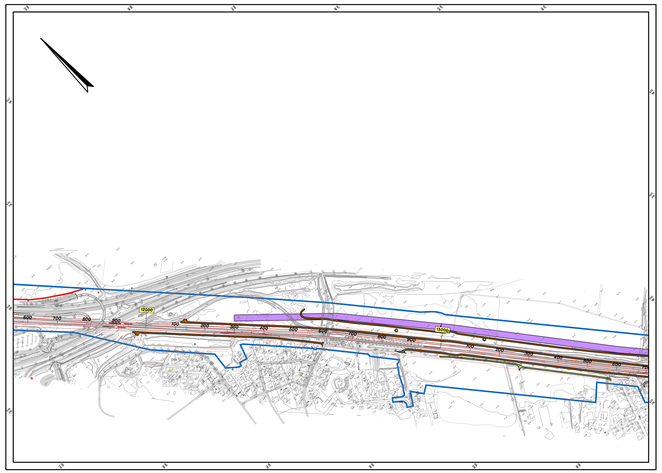


מפת מפתח :
קנ"מ 100,000 : 1





תכנון מחלף חב"ד
במסגרת ת.מ.א. 4\2\א\2



מקרא:

	גבול תחיל בנ
	גבול זכות הדרך
	גבול זכות נתל מתוכנן
	ציר מסילה מתוכננת
	רציף מתוכנן
	גבול רצועת רכבת
	מפגש כביש סימפון
	דרך שרות מתוכננת
	דרך תכניית מתוכננת
	שלד אספלט מתוכנן
	מעטה בטון מתוכנן
	מעטה מתוכנן
	תכנון עתיד
	עמודי להעתקה
	רצועה מתוכננת לשימוש מיטלט מערכות משאבי
	רצועה מתוכננת לחיפה

רכבת ישראל
מערך השמצה

הועדה הארצית לתכנון ולבניה
של תשתיות לאומיות

בעלי קרקע
מדינת ישראל ואחרים

יועצי התכנית

מנהל מדיניים

עורך התכנית

מודד מוסמך

יועצים

הרני מצהיר בזאת כי מדידת המפה, המשתקפים בתכנית זו, נערכה על ידי ביים ותיא הנקוה לפי הוראות נוהל מקאית (נוהאם להוראות חוק והתקנות (מודדים) שבתוקף.
ריום הגו הגבול המוסמך מדידה גרפית, לו כתוב בקבלו בתפר אלקטרוני, מדידה אלקטרונית מלאה, בדצם תעד עבודה זאת הנמלה.

שם המודד	מספר רישיון	חתימה	תאריך