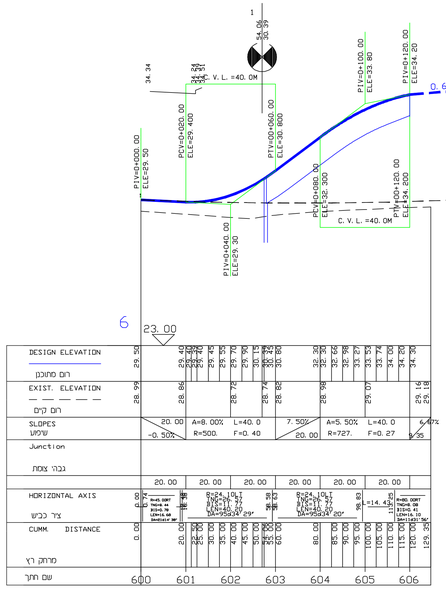
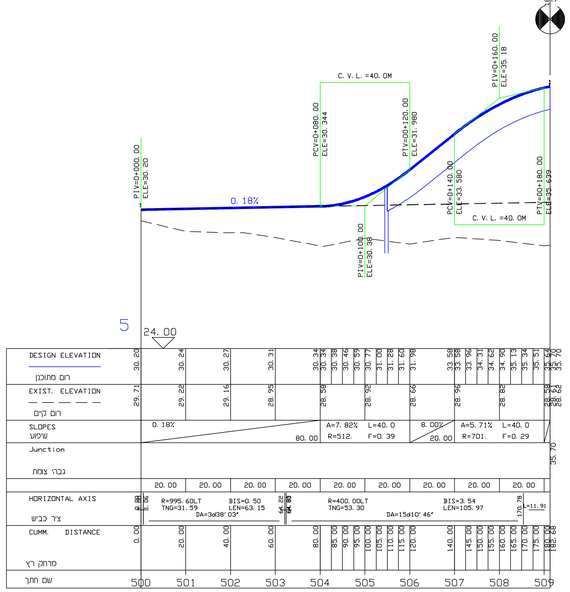
תכנית תת"ל 66 נוספה דרכים חתכים לאורך + רמפות 11:58:55 06/10/2015

רמפה מס' 1



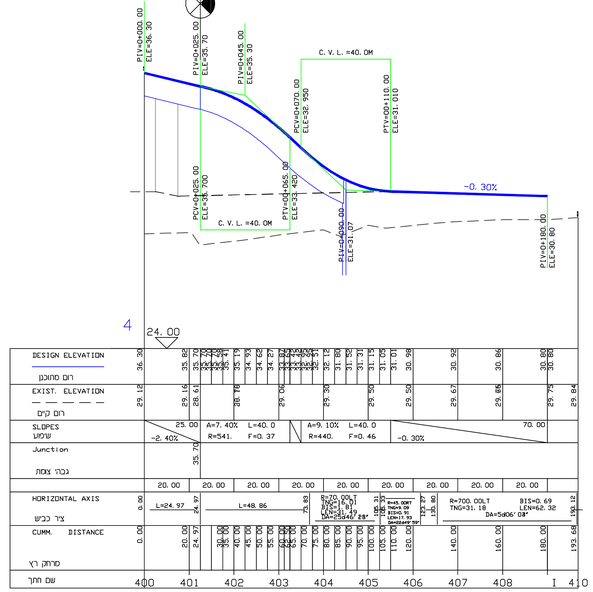
Scale 1: 100/ 1000 ROAD NAME: 6

רמפה מס' 2



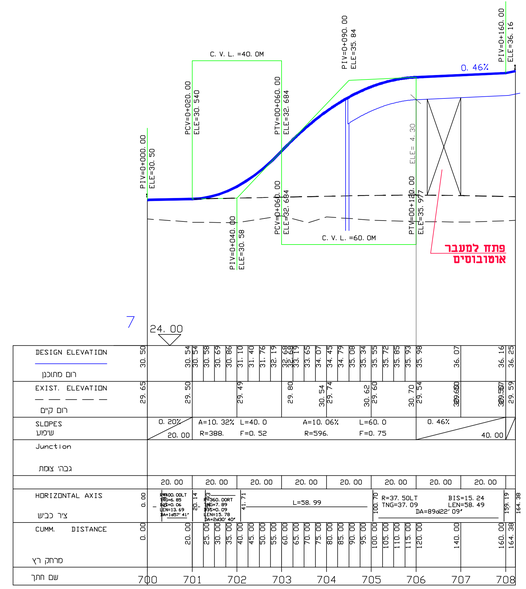
Scale 1: 100/ 1000 ROAD NAME: 5

רמפה מס' 3




Scale 1: 100/ 1000 ROAD NAME: 4

רמפה מס' 4

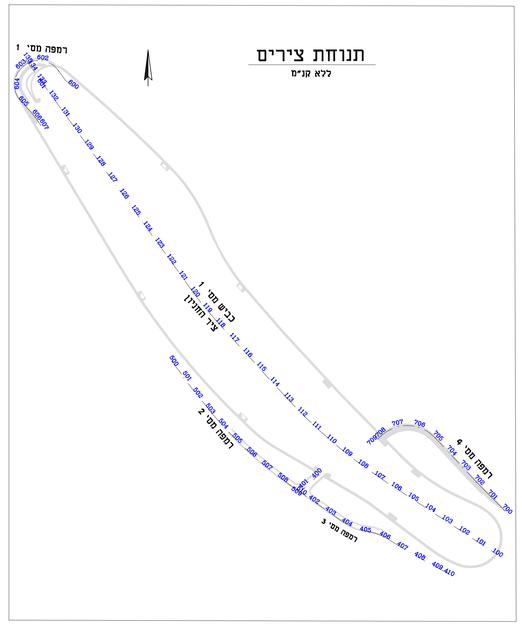


Scale 1: 100/ 1000 AXIS NAME: 7

כביש מס' 1
ציר החניון



Scale 1: 100/ 1000 ROAD NAME: 1



חוק התכנון והבנייה, התשכ"ה - 1965
תכנית לדוגמה לרשות מקומית
תת"ל 66
"חנה וסע" שפירים
חתכים לאורך + רמפות
נגיון
מתוך
מחוז: המרכז
מרחב תכנון מקומי: עמק לוד, מצפה אפק
רשות מקומית: מועצה אזורית עמק לוד
ישוב:
תאריך: 15/09/15
שם הנספח: חתכים לאורך + רמפות
קנ"מ: 1:1000/1000
תרשים סביבה: 1:50,000
שמות ותחתימות:
עורך התוכנית: שלמה גלבר
מרחב תכנון מקומי: מדיא

T:\6822 HANYON SHPIRIM-BUZIK\TNU-LAHV-2014\OREH-OLL-03.dwg, Model, 06/10/2015 11:20:34,
DWG To PDF.pc3